MAPAS CAMINHO FRANCÊS

+34 665 405 765
contato@tour4friends.com
facebook.com/tour4friends/
tour4friends.com

1ª ETAPA
SAINT-JEAN-PIED-DE PORT RONCESVALLES
22'7 KM

DISTANCIAS (POR UNTTO)

Saint-Jean-Pied-de-Port ..... 5,4 km
Untto 8,3
Cruce Cª Arneguy ..... 9,0 km
Roncesvalles

RONCESVALLES

A Larrasoaña

Don Simón

Alto de Ibañeta 1057 m

Repetidor T.V.

Ortzantzurieta

Mendichipi

Lapoeder 1440 m

Revuelta de Ferrán

Casa de Guardiano

Txangoa Ruinas de Elizarra

Aztobiscar

Usuaga

Izandorre

Fuente

Camino de Zabaleta

N. 135

Errenabeltza

Leizarateca

Urdanasburu

ESPAÑA

Camino de Arneguy

Estatua de la Virgen

DISTANCIAS (POR ARNEGUY)

Saint-Jean-Pied-de-Port ..... 8,0 km
Valcarlos ..... 10,5 km
Ibañeta ..... 1,0 km
Roncesvalles

Bianorre

Estación de Servicio

Valcarlos

Restaurante

FRANCIA

Orisson

Arbola Azpián

Arneguy

Frontón

Estación de Servicio

Las Ventas

Untto

Erreculuch

Nive

FRANCIA

Mendi Alaz

Porte de Espagne

Murallas

Rue

Murallas

Jardín

Othatzenea

Route du Marechal Harispe et de Napoleón

St. Michel

Mendialdia

Porte Notre Dame

Murallas

Río

Nive

Hotel

Farmacia

Hotel

Casas Siglos XVII-XIX

SAINT-JEAN-PIED-DE-PORT

Hotel

Piscina

Route N. 133 Ostabat - St. Palais

De Saint-Jean-le-Vieux

Río Petit

A Saint-Jean-le-Vieux

Porte d'Espagne

Nive

SAINT-JEAN-PIED-DE-PORT

De Ostebat C. 135 N. 133

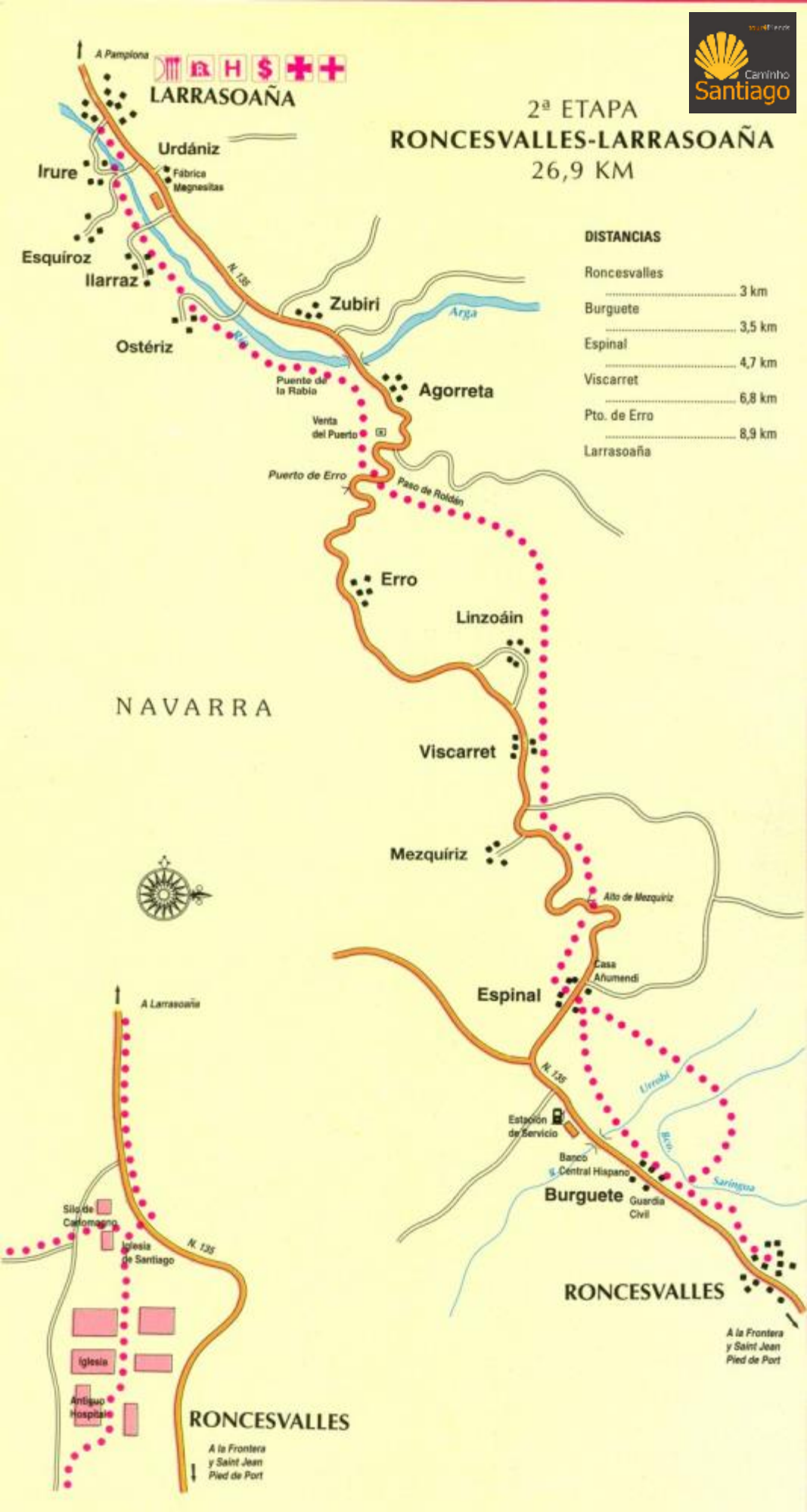
2ª ETAPA
RONCESVALLES-LARRASOAÑA
26,9 KM
DISTANCIAS
Roncesvalles ..... 3 km
Burguete ..... 3,5 km
Espinal ..... 4,7 km
Viscarret ..... 6,8 km
Pto. de Erro ..... 8,9 km
Larrasoaña
A Pamplona
LARRASOAÑA
Urdániz
Fábrica Magnesitas
Irure
Esquíroz
Ilarraz
Ostériz
N. 135
Zubiri
Arga
Río
Puente de la Rabia
Agorreta
Venta del Puerto
Puerto de Erro
Paso de Roldán
Erro
Linzoáin
NAVARRA
Viscarret
Mezquíriz
Alto de Mezquíriz
Casa Añumendi
Espinal
A Larrasoaña
N. 135
Estación de Servicio
Urrobi
Río
Saringoa
Banco Central Hispano
Burguete
Guardia Civil
Silo de Carlomagno
Iglesia de Santiago
N. 135
Iglesia
Antiguo Hospital
RONCESVALLES
A la Frontera y Saint Jean Pied de Port
RONCESVALLES
A la Frontera y Saint Jean Pied de Port

A Puente La Reina
CIZUR
Cizur Mayor
Cizur Menor
A-15 a Tafalla
N. 111
Carretera
Río
Sadar
de
Circunvalación
A-15 a Irurzun
A Irurzun
Puente de la Magdalena
PAMPLONA
N. 135
Arga
Burlada
Olatz
Villava
Río
Huarte
Monte Miravalles
La Trinidad de Arre
Arre
Túnel
Arleta
Casetas de la luz
Virgen de las Nieves
Monte Nárvat
Ulzama
N. 135-A
Río
Zabaldica
Iroz
N. 135
A Ostiz
Zuriáin
Guenduláin
Ilúrdoz
Aquerreta
Idoy
Sarazibar
Irure
LARRASOAÑA
A Roncesvalles
3ª ETAPA
LARRASOAÑA-
PAMPLONA (CIZUR)
19'5 KM
DISTANCIAS
Larrasoaña ..... 3,7 km
Zuriáin ..... 5,4 km
La Trinidad ..... 6,2 km
Pamplona ..... 4,2 km
Cizur
NAVARRA
A Pamplona
Arga
N. 135
Claveria
Venta de Aquerreta
LARRASOAÑA
Río
A Roncesvalles

PUENTE LA REINA
GARES
C. Cerco Viejo
Iglesia del Crucifijo
Iglesia de Santiago
Biblioteca
Iglesia de S. Pedro
Ayuntamiento
C. Cerco Nuevo
Paseo de los Fueros
Pº Fray Vicente de Bernedo
Río
Arga
Comendadores
A Estella
PUENTE LA REINA
4ª ETAPA
CIZUR-PUENTE LA REINA
19 KM
Caminho Santiago
NAVARRA
DISTANCIAS
Cizur ..... 6,1 km
Zariquiegui ..... 5,8 km
Uterga ..... 4,3 km
Obanos ..... 2,8 km
Puente la Reina
Ermita San Salvador
Mto. a los Caminos
Cruce de los Caminos Aragonés y Navarro
Monumento al peregrino
Obanos
Crucero
Muruzábal
N. 111
Uterga
Alto del Perdón 734 m
Molino de Viento
Sierra del Perdón
Fuente de Reniega
Zariquiegui
Asráin
Charco
Palacio
Galar
Cementerio
Guenduláin
Arroyo
Sembrado
Poste Eléctrico
Sembrado
Urbanización
Cizur Menor
CIZUR
Cizur Mayor
Carretera de Circunvalación
A Puente La Reina
Chalets
Cizur Menor
Cizur Mayor
Asador
Ikastola
Ciudad Universitaria
Plaza de Toros
Ciudadela
PAMPLONA

Caminho Santiago
ESTELLA
Iglesia de San Pedro de Lizarra
Pl. Pía de la Paz
Antiguo Hospital
Iglesia San Juan
Pl. de Santiago
Pl. de los Fueros
Pl. de S. Miguel
Pl. del Mercado Viejo
Iglesia San Miguel
Paseo de la Inmaculada
Correos y Telégrafos
Pl. San Francisco de Asís
Puente de la Cárcel
Iglesia del Santo Sepulcro
Pl. de la Coronación
Estación de Autobuses
Pl. San Martín
Iglesia de Santa María Jus del Castillo
Iglesia de San Pedro de La Rua
Convento de Santo Domingo
Convento Santa Clara
Portal de Castilla
Ega
Río
A Los Arcos
Monolito
Palacio de los Reyes
S. Pedro
ESTELLA
Verbo Divino
Ermita de S. Miguel
Río Iranzu
Villatuerta
Arandigoyen
Fuente
N 111
5ª ETAPA
PUENTE LA REINA-ESTELLA
19 KM
Lácar
Salado
Lorca
Fuente
A Allóz
Molino
Túnel
Puente Medieval
Ruinas
Acueducto
Casa
Ruinas de Urbe
Puente Romano
Calzada Romana
Cirauqui
NAVARRA
Cementerio
Mañeru
Cruz
Merendero
Arga
Eunea
Convento Reparadores
Iglesia del Crucifijo
Iglesia de Santiago
PUENTE LA REINA
A Pamplona
DISTANCIAS
Puente la Reina
4,5 km
Mañeru
2,7 km
Cirauqui
5,3 km
Lorca
4,3 km
Villatuerta
2,2 km
Estella

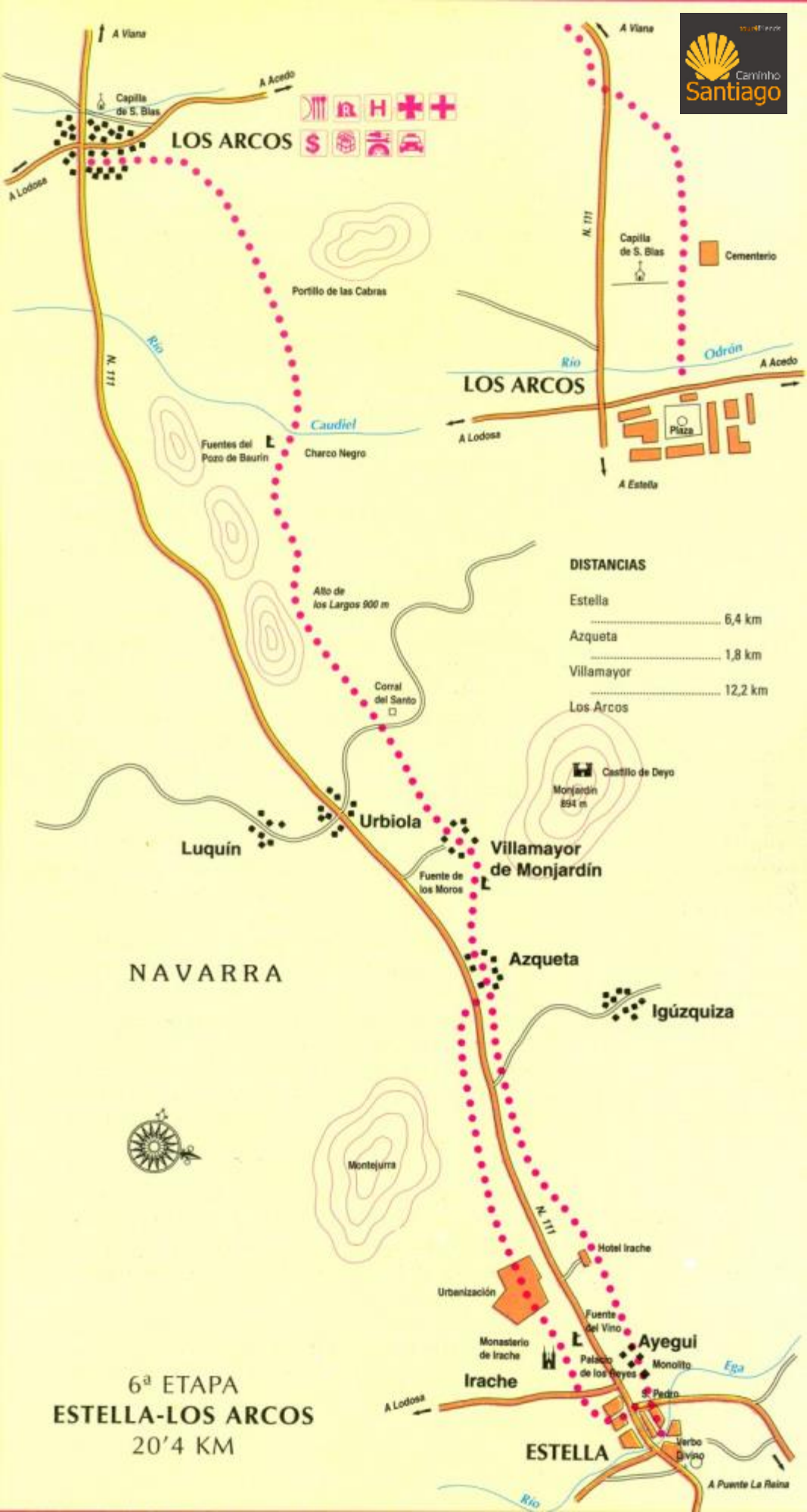

6ª ETAPA
ESTELLA-LOS ARCOS
20'4 KM

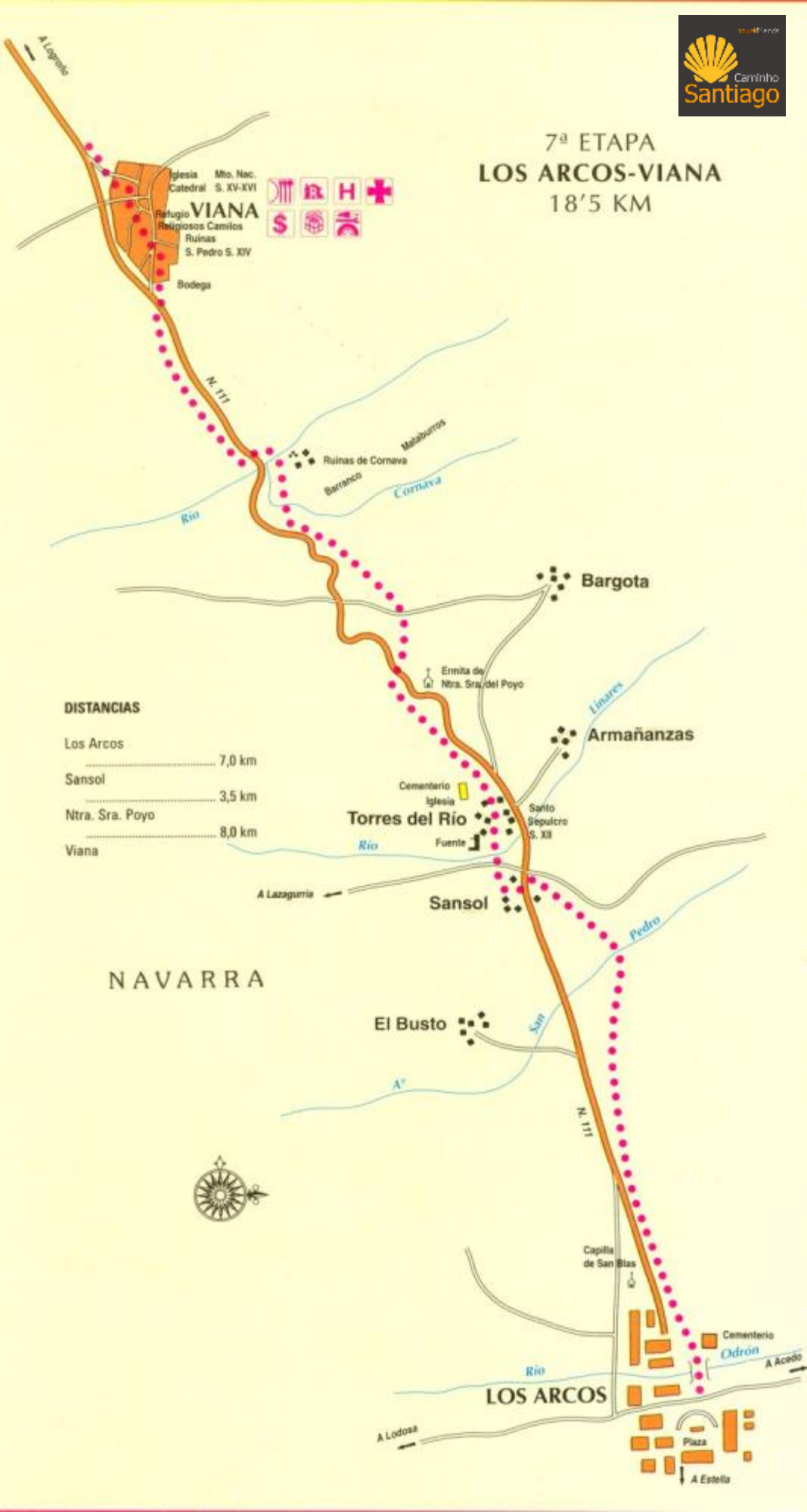
Caminho Santiago
7ª ETAPA
LOS ARCOS-VIANA
18'5 KM
A Logroño
Iglesia Catedral
Mto. Nac. S. XV-XVI
Refugio Religiosos Camilos
VIANA
Ruinas S. Pedro S. XIV
Bodega
N. 111
Mataburos
Ruinas de Cornava
Barranco
Cornava
Río
Bargota
Ermita de Ntra. Sra. del Poyo
Limares
Armañanzas
DISTANCIAS
Los Arcos ..... 7,0 km
Sansol ..... 3,5 km
Ntra. Sra. Poyo ..... 8,0 km
Viana
Cementerio
Iglesia
Torres del Río
Santo Sepulcro S. XII
Fuente
Río
A Lazagurria
Sansol
Pedro
NAVARRA
El Busto
San
A°
N. 111
Capilla de San Blas
Cementerio
Odrón
A Acedo
Río
LOS ARCOS
A Lodosa
Plaza
A Estella

8ª ETAPA
VIANA-NAVARRETE
21 KM
LA RIOJA
ÁLAVA
NAVARRA
NAVARRETE
Ruinas de la Orden de S. Juan de Acre s. XII
A Los Arcos
N. 120
A Nájera
Religiosos Camilos
NAVARRETE
Ruinas del Antiguo Hospital
A Miranda de Ebro
A Haro
Fuenmayor
A-68
Puente
N. 232
Alto de La Grajera
Estación de Servicio
Pantano de La Grajera
Estación de Servicio
Ebro
A Soria
N. 111
Cementerio
LOGROÑO
Oyón
DISTANCIAS
Viana ..... 9 km
Logroño ..... 12 km
Navarrete
Ruinas Romanas
Cerro Cantabria
Río
Pantano de las Cañas
Perizuelas
Ermita de La Trinidad de Cuevas
Cementerio
A Zaragoza
Refugio Religiosos Camilos
Fábrica
VIANA
Iglesia Catedral
Mto. Nac. S. XV-XVI
Ruinas S. Pedro S. XIV
Bodegas
A Los Arcos
Caminho Santiago

Najerilla
Arrabal de San Fernando
Cuartel Guardia Civil
Convento de Sta. Elena
Antigua Iglesia de San Miguel
Monasterio Santa María La Real
Parroquia de Sta. Cruz
Río
NÁJERA
A Sto. Domingo de la Calzada
9ª ETAPA
NAVARRETE-NÁJERA
14 KM
Ruinas de San Jaime
NÁJERA
Al Monasterio de Valvanera
Sta. María la Real
Najerilla
Tricio
N. 120
Poema Escrito
Yalde
A San Asensio
Gravera
Huércanos
Alesón
Choza
Río
Poyo Roldán
Restos exploración petrolífera
DISTANCIAS
Navarrete ..... 12,0 km
Gravera ..... 2,0 km
Nájera
LA RIOJA
Casa
Alto de San Antón
Ventosa
Sotés
N. 120
Hornos de Moncalvillo
Cementerio portada S. XII
Religiosos Camilos
NAVARRETE
Ruinas Antiguo Hospital
A Logroño

10ª ETAPA
NÁJERA-
STO. DOMINGO DE LA CALZADA
20,7 KM

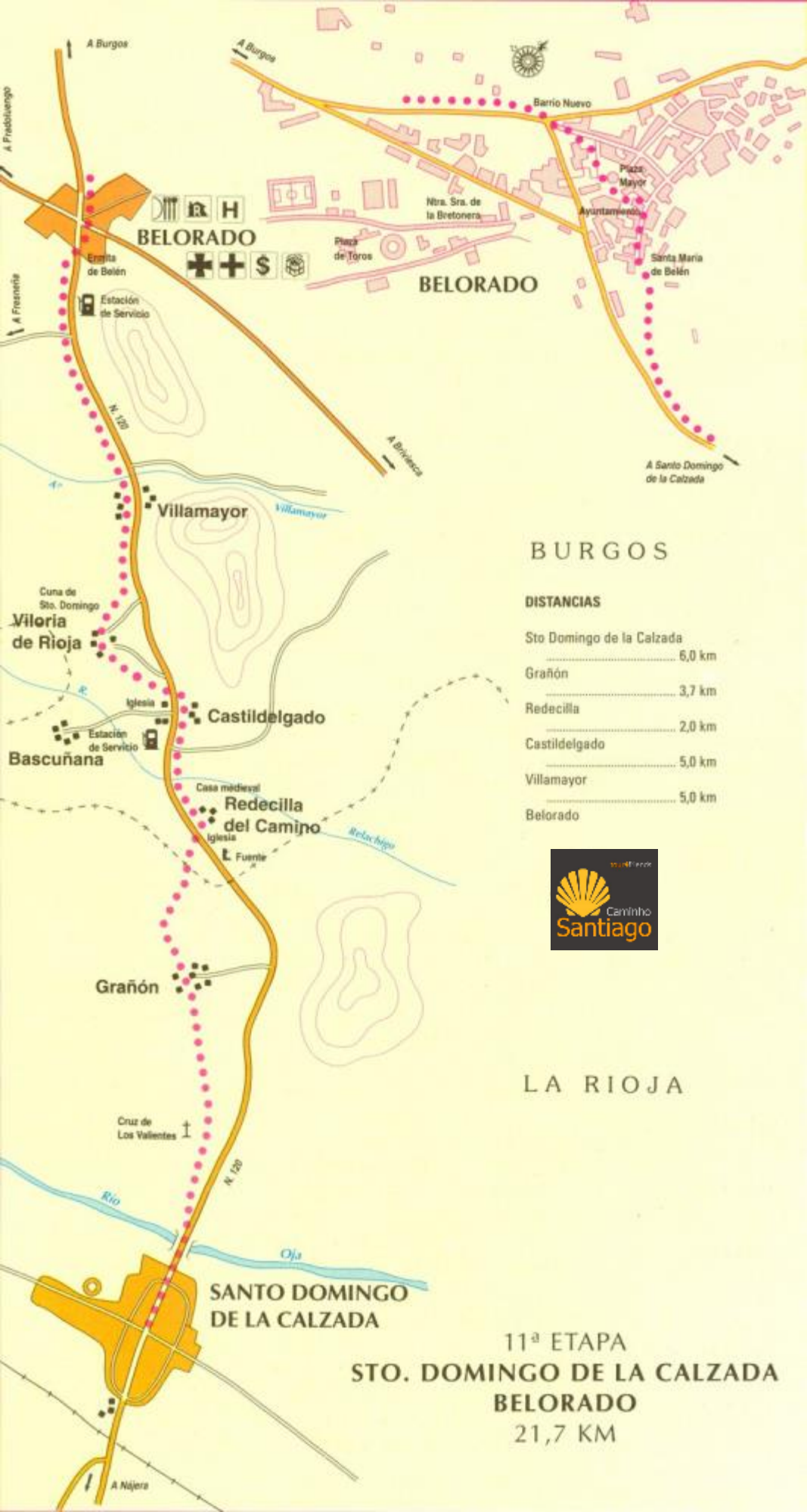

DISTANCIAS

Sto Domingo de la Calzada	6,0 km
Grañón	3,7 km
Redecilla	2,0 km
Castildelgado	5,0 km
Villamayor	5,0 km
Belorado	

11ª ETAPA

STO. DOMINGO DE LA CALZADA
BELORADO

21,7 KM

12ª ETAPA
BELORADO
SAN JUAN DE ORTEGA
23,7 KM
A Burgos
Santovenia
Iglesia
Mto. Nac. S. XII
SAN JUAN
DE ORTEGA
Camino
Santiago
N. 120
Ermita
de Valdefuentes
Puerto de
La Pedraja
1150 m
Monumento
a los Caídos
BURGOS
Fuente de
Mojapan
Ermita
Virgen de Oca
Iglesia
Villafranca
Montes de Oca
Hospital
de San Antón
Teléfonos
Correos
Río
Oca
Ábside
de San Felices
Espinosa
del Camino
Ermita
de S. Roque
Cementerio
Villambistia
Ermita
Virgen de la Peña
Tosantos
A San Miguel
del Pedroso
N. 120
A Briviesca
Río
Tirón
A San Miguel
del Pedroso
BELORADO
A Sto. Domingo
de la Calzada
DISTANCIAS
Belorado ..... 5,1 km
Tosantos ..... 1,6 km
Villambistia ..... 1,7 km
Espinosa ..... 3,2 km
Villafranca ..... 5,7 km
Eta. Valdelafuentes ..... 6,4 km
S. Juan de Ortega

13ª ETAPA
SAN JUAN DE ORTEGA
BURGOS
22,8 KM

DISTANCIAS

S. Juan de Ortega	3,7 km
Agés	2,6 km
Atapuerca	8,5 km
Orbaneja	3,0 km
Villafría	5,0 km
Burgos	

BURGOS

A Madrid
BURGOS
A-1
Estación de Servicio
Gamonal
Arlanzón
N. 120
N. 1
Hostal
Villafría
Aeródromo
Río
Pico
Río
A-1
Ferrocarril Madrid-Irún
Orbaneja
San Medel
Río
Vena
Rubena
Cardeñuela
Torres de Telefónica
Ibeas de Juarros
Villalval
Olmos de Atapuerca
A Vitoria
Sierra de Atapuerca
Terrenos apotados
A Miranda de Ebro
Atapuerca
N. 120
Puente de San Juan
Zalduendo
Iglesia
Fuente agua potable
Agés
Ermita del Rebollo
Barrios de Colina
Santovenia
SAN JUAN DE ORTEGA
A Logroño

A Frómista
A Villasandino
CASTROJERIZ
Colegiata de la Virgen del Manzano
A Astudillo
Convento San Antón
Fuente de los Peregrinos
San Miguel (Ruinas)
Molino del Cubo
Iglesia
Hontanas
Castellanos de Castro
Crucero
Villadiego
A Iglesias
Olmillos de Sasamón
N 120
A Olmillos
San Juan
Castillo (Ruinas)
Museo Parroquial
Sto. Domingo
A Melgar de Fernamental
Colegiata de la Virgen del Manzano
DISTANCIAS
Burgos ..... 7,0 km
Villalbilla ..... 2,0 km
Tardajos ..... 2,1 km
Rabé de las Calzadas ..... 8,0 km
Hornillas del Camino ..... 10,2 km
Hontanas ..... 9,0 km
Castrojeriz
Fuente Sambol
Arroyo San Bol
Depósito de Agua
Río
Hornillos del Camino
A Estepar
Cuesta de Matamulos
Villanueva de Argaño
Hornazuela
BURGOS
Plataforma Sondeos
Cementerio
Ermita
Rabé de Las Calzadas
Las Quintanillas
Río Urbel
Río
Tardajos
P. P. Paúles
N 120
Villalbilla de Burgos
Río Ubierna
Arlanzón
Molino de Las Huelgas
Puente de Malatos
Hospital del Rey
BURGOS
Caminho Santiago
14ª ETAPA
BURGOS-CASTROJERIZ
38'3 KM

16ª ETAPA

FRÓMISTA

CARRIÓN DE LOS CONDES

19'2 KM

DISTANCIAS

Castrojeriz ..... 11,2 km
Itero de la Vega ..... 8,4 km
Boadilla ..... 5,4 km
Frómista

SAHAGÚN
A Cea
A Villada
Cea
Túnel
Valderaduey
Ermita Virgen del Puente
Villalebrin
Rio
Sequillo
Rio
San Nicolás del Reál Camino
Riosequillo
LEÓN
N 120
Moratinos
Templarios
Terradillos de Templarios
Ledigos
A Saldaña
A Población del Arroyo
Cueza
PALENCIA
Mont. Sta. Mª de las Tiendas (Restos)
Bodegas
Calzadilla de la Cueza
Iglesia
Torre y cementerio
Rio
Quintanilla de la Cueza
N 120
Valdemonio
Seco
A Porto Amargo
Bustillo del Páramo
Cervatos de la Cueza
Rio
Fuente
Villotilla
Ruinas Abadía de Benevivere
Abadía de Abajo
A Saldaña
Calzada de los Molinos
Ermita de La Piedad
Carrión
Monasterio de S. Zoilo
Rio
A Palencia
Monasterio de Sta. Clara
CARRIÓN DE LOS CONDES
A Osorno
Arco de San Benito
Madres Benedictinas
Iglesia de la Peregrina
San Tirso
Ayuntamiento
San Lorenzo
S. Juan de Sahagún
Iglesia de la Trinidad
SAHAGÚN
San Benito
Estación F.C.
Caminho Santiago
17ª ETAPA
CARRIÓN DE LOS CONDES
SAHAGÚN
37'6 KM
DISTANCIAS
Carrión de los Condes ..... 4,0 km
Abadía Benevivere ..... 12,3 km
Calzadilla ..... 6,2 km
Ledigos ..... 2,5 km
Terradillos ..... 3,1 km
Moratinos ..... 2,5 km
San Nicolás ..... 7,0 km
Sahagún

Caminho Santiago

18ª ETAPA

SAHAGÚN

EL BURGO RANEROS

17,7 KM

19ª ETAPA
EL BURGO RANEROS MANSILLA DE LAS MULAS
18,6 KM

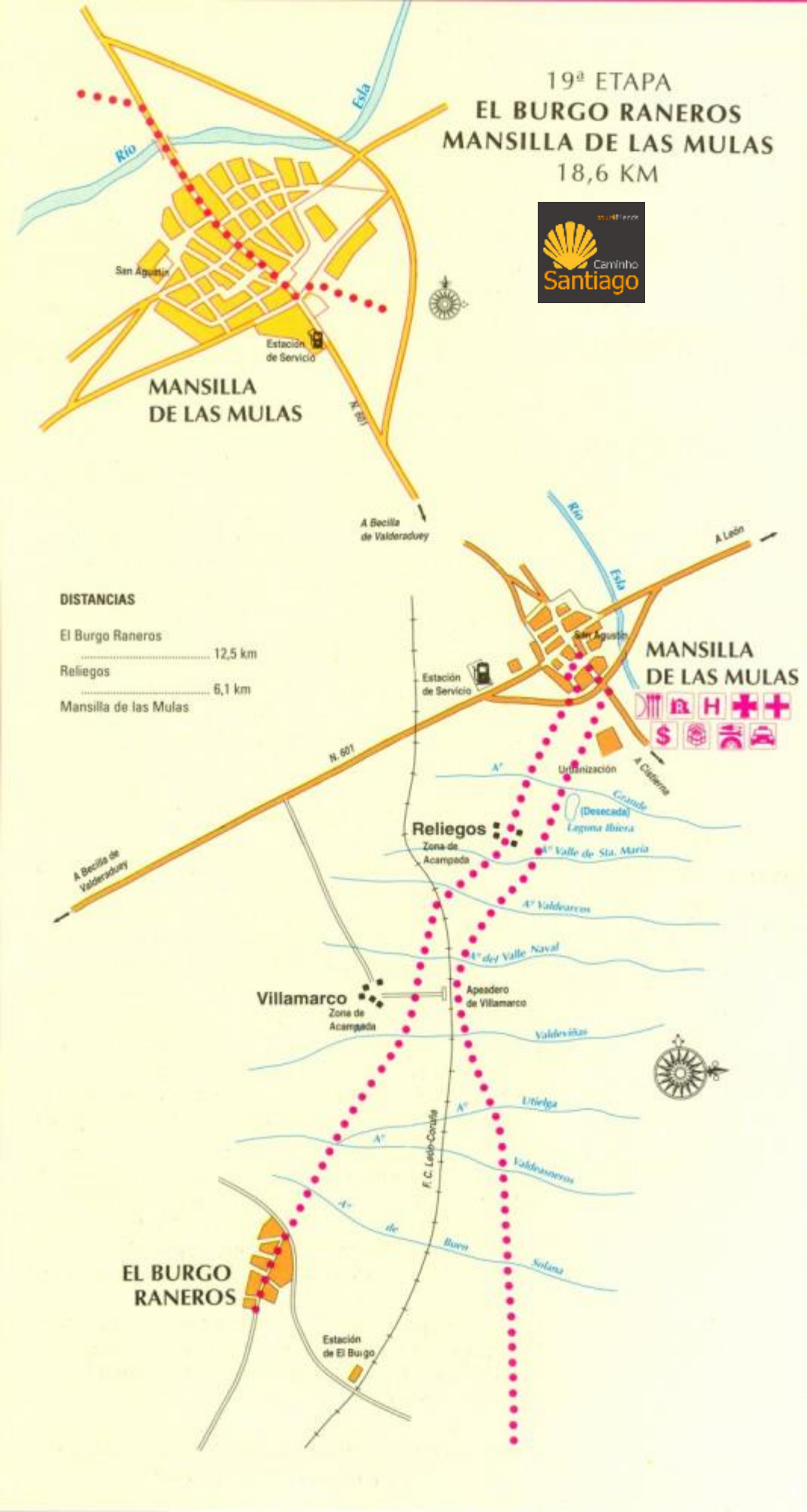

DISTANCIAS

El Burgo Raneros ..... 12,5 km

Reliegos ..... 6,1 km

Mansilla de las Mulas

20ª ETAPA
MANSILLA DE LAS MULAS
LEÓN
17 KM

DISTANCIAS

Mansilla de las Mulas	
	4,0 km
Villamoros	
	1,8 km
Villarente	
	4,6 km
Arcahueja	
	1,0 km
Valdelafuente	
	3,6 km
Puente Castro	
	2,0 km
León	

21ª ETAPA
LEÓN-VILLADANGOS
21'8 KM

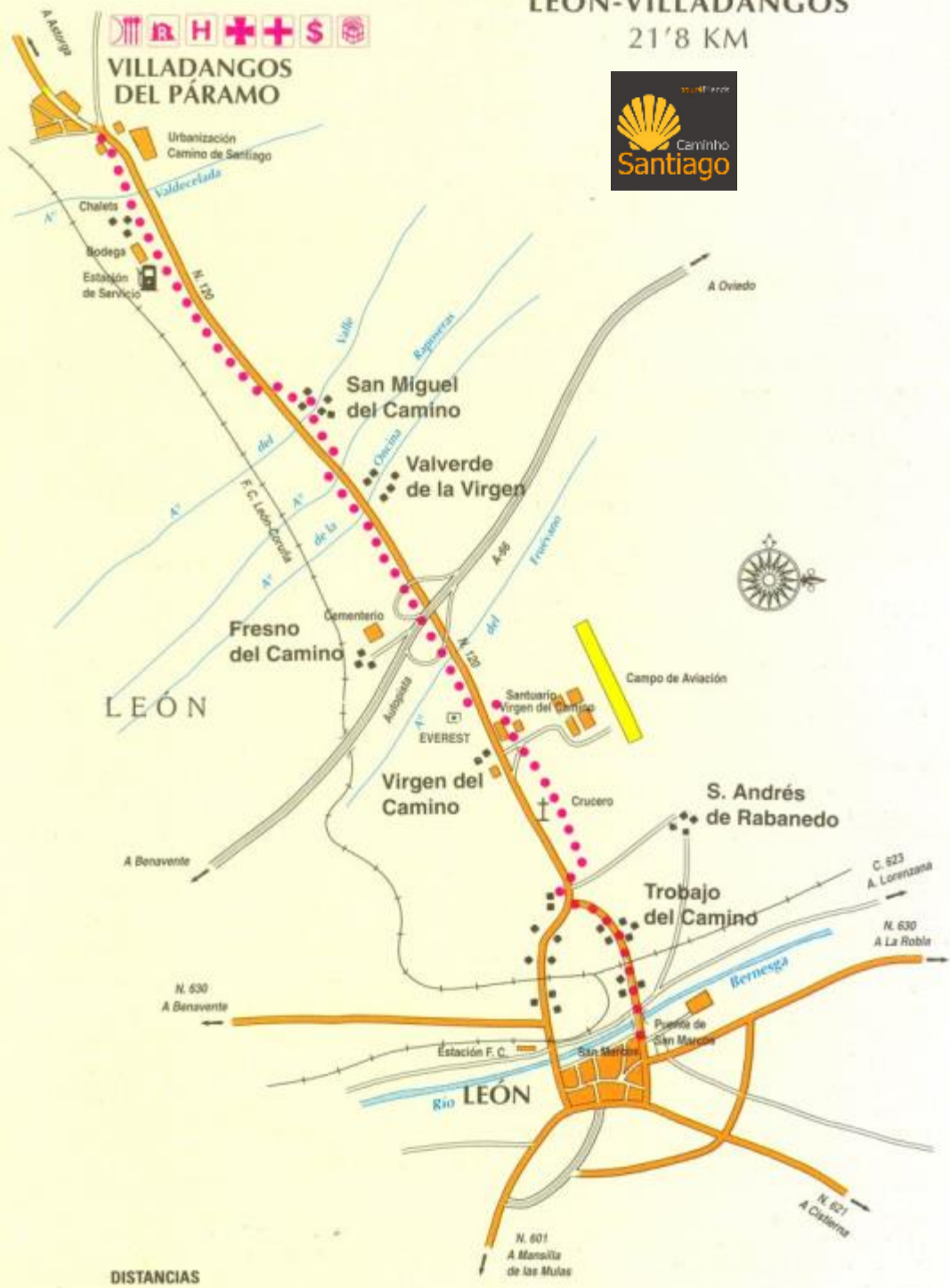

DISTANCIAS

León	
Trobajo del Camino	4,6 km
Virgen del Camino	2,7 km
Valverde	3,7 km
San Miguel del Camino	3,0 km
Villadangos del Páramo	7,8 km

ASTORGA
A Rabanal
N. VI
Plaza de Toros
ASTORGA
A La Bañeza
N. VI
Puente Romano
Río
Tuerto
San Justo de la Vega
San Román de la Vega
Crucero de S. Toribio
N. 120
Sierra de La Paloma
Grillo
Santibánez
Estebánez de la Calzada
Villares de Órbigo
Canal
Benavides de Órbigo
A Viloria
Hotel
Hospital de Órbigo
Ayuntamiento
Río
Pte. Romano
Puente de Órbigo
Órbigo
Sta. Marina del Rey
A Camino
A Sta. María del Páramo
San Martín del Camino
Huerga
Celadilla del Páramo
A Bustillo
de la
Canal
del
Páramo
Riego
Lavadero
N. 120
VILLADANGOS DEL PÁRAMO
Urbanización Ct. de Santiago
A León
ASTORGA
La Corona
S. Pedro
N. VI
A Madrid
Catedral
Sta. Marta
Muralla
Romana
A León
S. Francisco
22ª ETAPA
VILLADANGOS-ASTORGA
26 KM
Caminho Santiago
LEÓN
DISTANCIAS
Villadangos del Páramo ..... 3,0 km
San Martín ..... 7,0 km
Puente Órbigo ..... 2,0 km
Villares ..... 2,0 km
Santibáñez ..... 8,0 km
San Justo ..... 4,0 km
Astorga

23ª ETAPA
ASTORGA
RABANAL DEL CAMINO
19'5 KM

DISTANCIAS

Astorga	4,0 km
Murias	4,5 km
Sta. Catalina	4,2 km
El Ganso	3,8 km
Puente de Pañote	3,0 km
Rabanal del Camino	

24ª ETAPA

RABANAL DEL CAMINO
PONFERRADA

32 KM

25ª ETAPA
PONFERRADA
VILLAFRANCA DEL BIERZO
23'3 KM

26ª ETAPA

VILLAFRANCA DEL BIERZO O CEBREIRO

27'8 KM

DISTANCIAS

Villafranca del Bierzo	
Trabadelo	9,5 km
Ambasmestas	5,1 km
Herrerías	5,0 km
La Faba	3,7 km
O Cebreiro	4,5 km

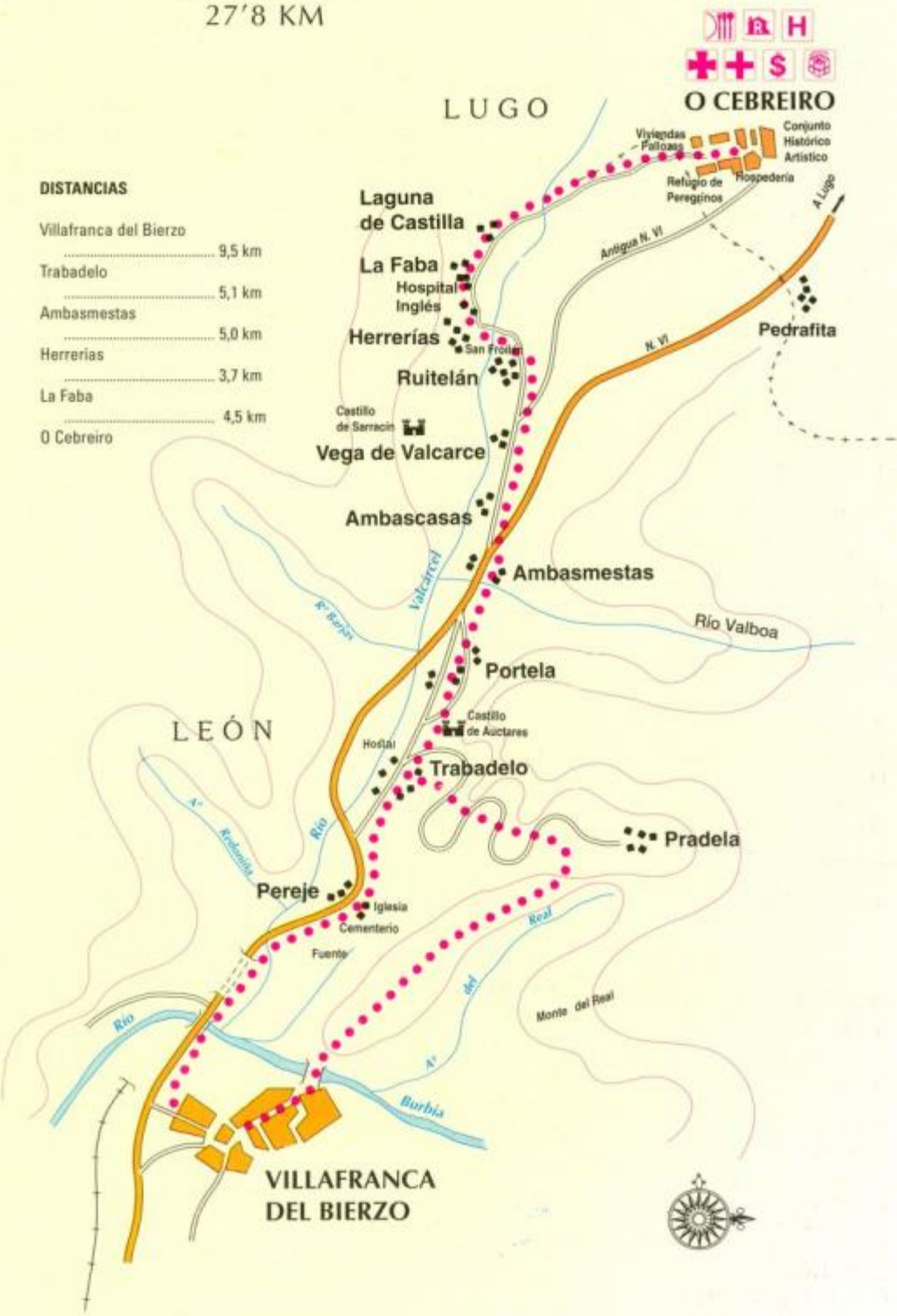

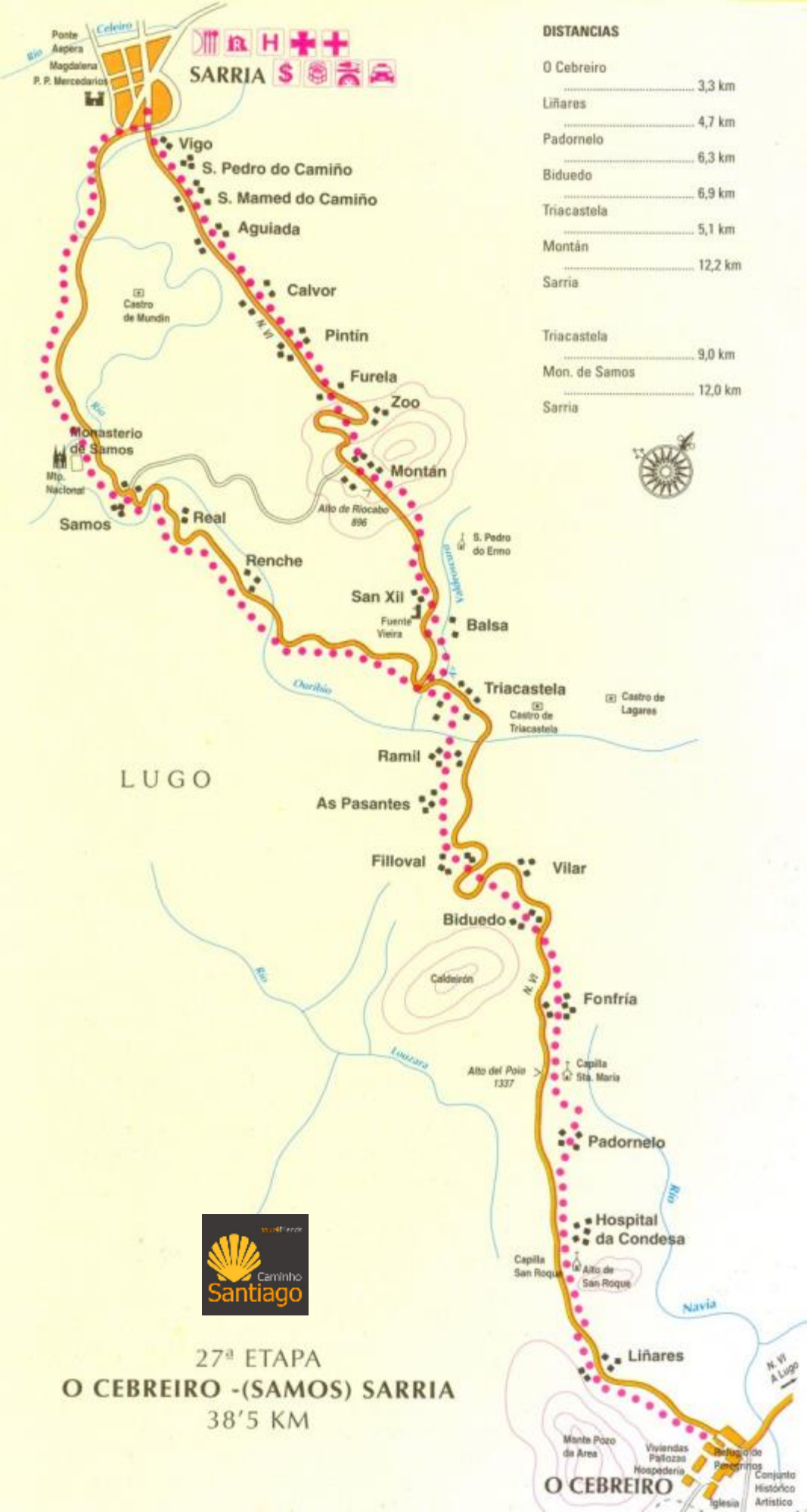

27ª ETAPA

O CEBREIRO -(SAMOS) SARRIA

38'5 KM

PORTOMARÍN
Embalse de Belesar
Río
Miño
Cortapezas
Parador San Juan
Palacio del Conde
Paxo de Berbetoros
Vilacha
Parrocha
Ruinas Monasterio
Moutras
Loio
Mercadoiro
Moimentos
Francos Iglesia
Peña do Cervo
C. 535
Loio
Rozas
Pena
Mirallos
Ferreiros
Cementerio
A 100 mts Refugio
Río
Morgade
Brea
Chelo
Lavandeira
Cortiñas
Variante
Peruscallo
Leimán
Domiz
Xisto
Mouzós
Mercado
Rente
Iglesia de Santiago
Barbadelo
Vilei
Sancti Michaelis
Río
Ponte Aspera
Celeiro
Cementerio
Madalena
F.C. Madrid a La Coruña
SARRIA
Sarria
Río
LUGO
DISTANCIAS
Sarria ..... 3,4 km
Barbadelo ..... 2,8 km
Mouzós ..... 3,1 km
Lavandeira ..... 12,5 km
Portomarín
28ª ETAPA
SARRIA-PORTOMARÍN
21'5 KM
Caminho Santiago

29ª ETAPA
PORTOMARÍN-PALAS DE REI
23'9 KM

DISTANCIAS

Portomarín	
Gonzar	7,6 km
Ventas de Narón	5,2 km
Eirexe	4,1 km
Palas de Rei	7 km

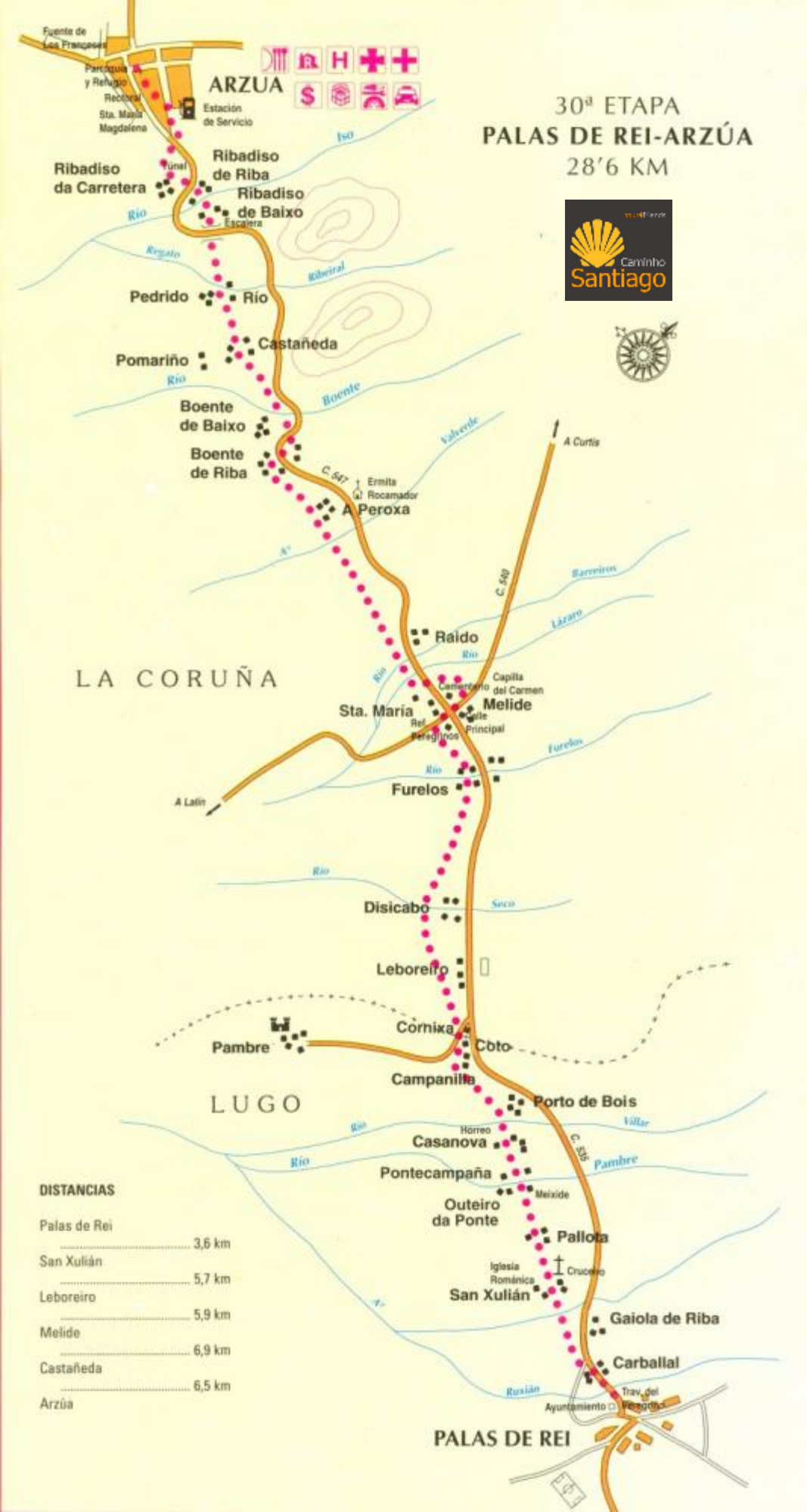
30ª ETAPA
PALAS DE REI-ARZÚA
28'6 KM
Camino Santiago
ARZUA
Fuente de Los Franceses
Parroquia y Refugio
Rectoral Sta. María Magdalena
Estación de Servicio
Iso
Ribadiso da Carretera
Túnel
Ribadiso de Riba
Ribadiso de Baixo
Escalera
Rio
Regato
Ribeiral
Pedrido
Río
Castañeda
Pomariño
Boente
Boente de Baixo
Boente de Riba
Valverde
C. 547
Ermita
Rocamador
A Peroxa
A Curtis
C. 549
Barreiros
Lázaro
Raido
LA CORUÑA
Capilla del Carmen
Cementerio
Melide
Sta. María
Calle Principal
Ref. Peregrinos
Furelos
A Lalín
Disicabo
Seco
Leboreiro
Cornixa
Pambre
Coto
Campanilla
LUGO
Porto de Bois
Villar
Horreo
Casanova
C. 535
Pambre
Pontecampaña
Meixide
Outeiro da Ponte
Pallota
Iglesia Románica
Crucero
San Xulián
Gaiola de Riba
Carballal
Rusián
Trav. del Peregrino
Ayuntamiento
PALAS DE REI
DISTANCIAS
Palas de Rei
3,6 km
San Xulián
5,7 km
Leboreiro
5,9 km
Melide
6,9 km
Castañeda
6,5 km
Arzúa

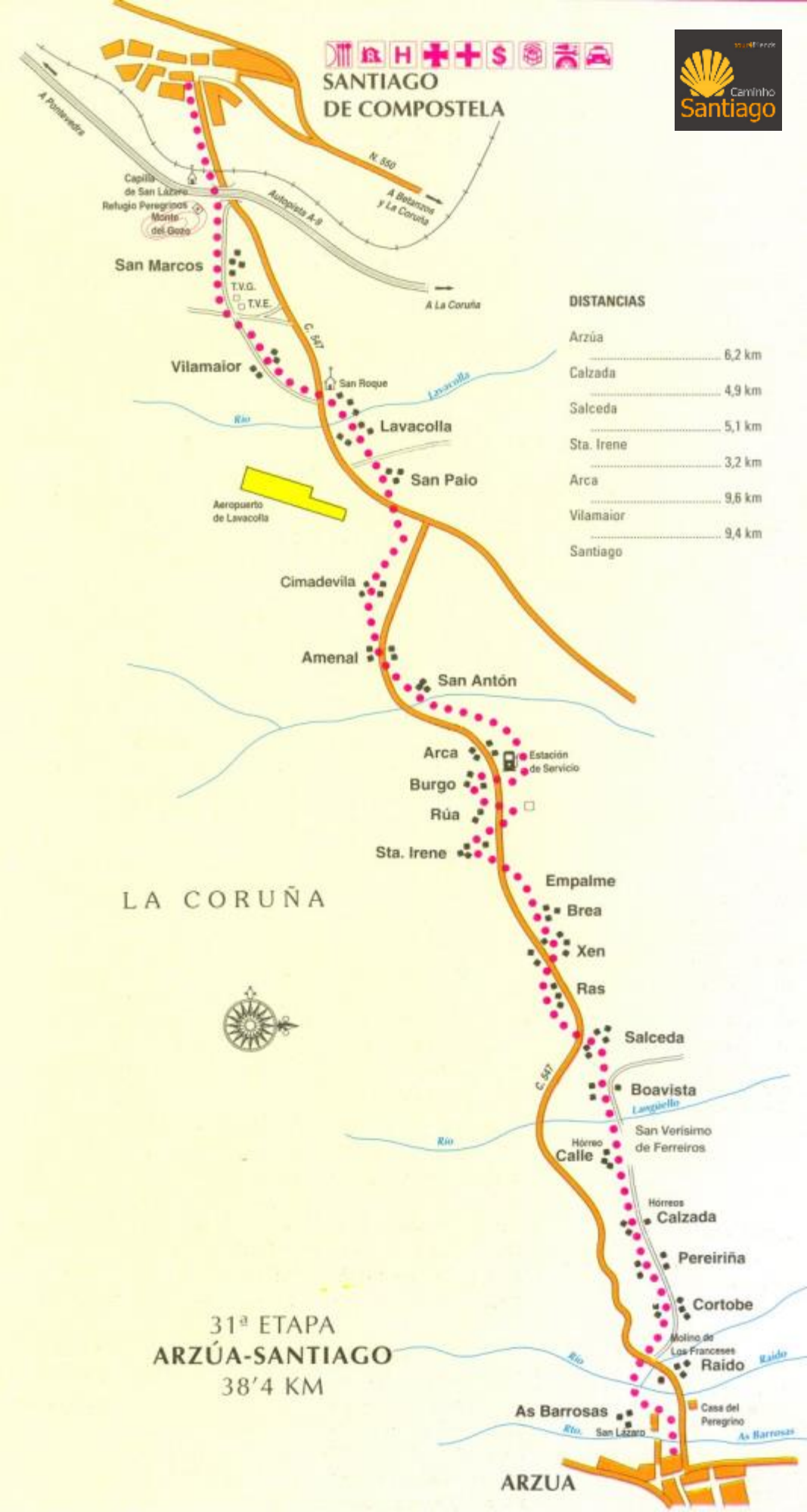
SANTIAGO
DE COMPOSTELA
A Pontevedra
N. 550
A Betanzos
y La Coruña
Capilla
de San Lázaro
Refugio Peregrinos
Monte
del Gozo
Autopista A-9
San Marcos
T.V.G.
T.V.E.
A La Coruña
C. 547
Vilamaior
San Roque
Lavacolla
Río
Lavacolla
San Paio
Aeropuerto
de Lavacolla
Cimadevila
Amenal
San Antón
Arca
Estación
de Servicio
Burgo
Rúa
Sta. Irene
LA CORUÑA
Empalme
Brea
Xen
Ras
Salceda
C. 547
Boavista
Langüello
Río
San Verísimo
de Ferreiros
Hórreo
Calle
Hórreos
Calzada
Pereiriña
Cortobe
Molino de
Los Franceses
Río
Raido
Raido
As Barrosas
Río
San Lázaro
Casa del
Peregrino
As Barrosas
ARZUA
DISTANCIAS
Arzúa
6,2 km
Calzada
4,9 km
Salceda
5,1 km
Sta. Irene
3,2 km
Arca
9,6 km
Vilamaior
9,4 km
Santiago
31ª ETAPA
ARZÚA-SANTIAGO
38'4 KM